Notiz:

Pin Icons zeigen die nächsten Sehenswürdigkeiten in der Nähe.

Falls man direkt bei einer Sehenswürdigkeit ist, kann man auch direkt dorthin, über den Button "Sehenswürdigkeit in der Nähe erkennen", gelangen (Radius z. B. 50m).

Auch kann man manuell den zugehörigen QR-Code scannen, falls es dort z. B. mehrere Sehenswürdigkeiten gibt.

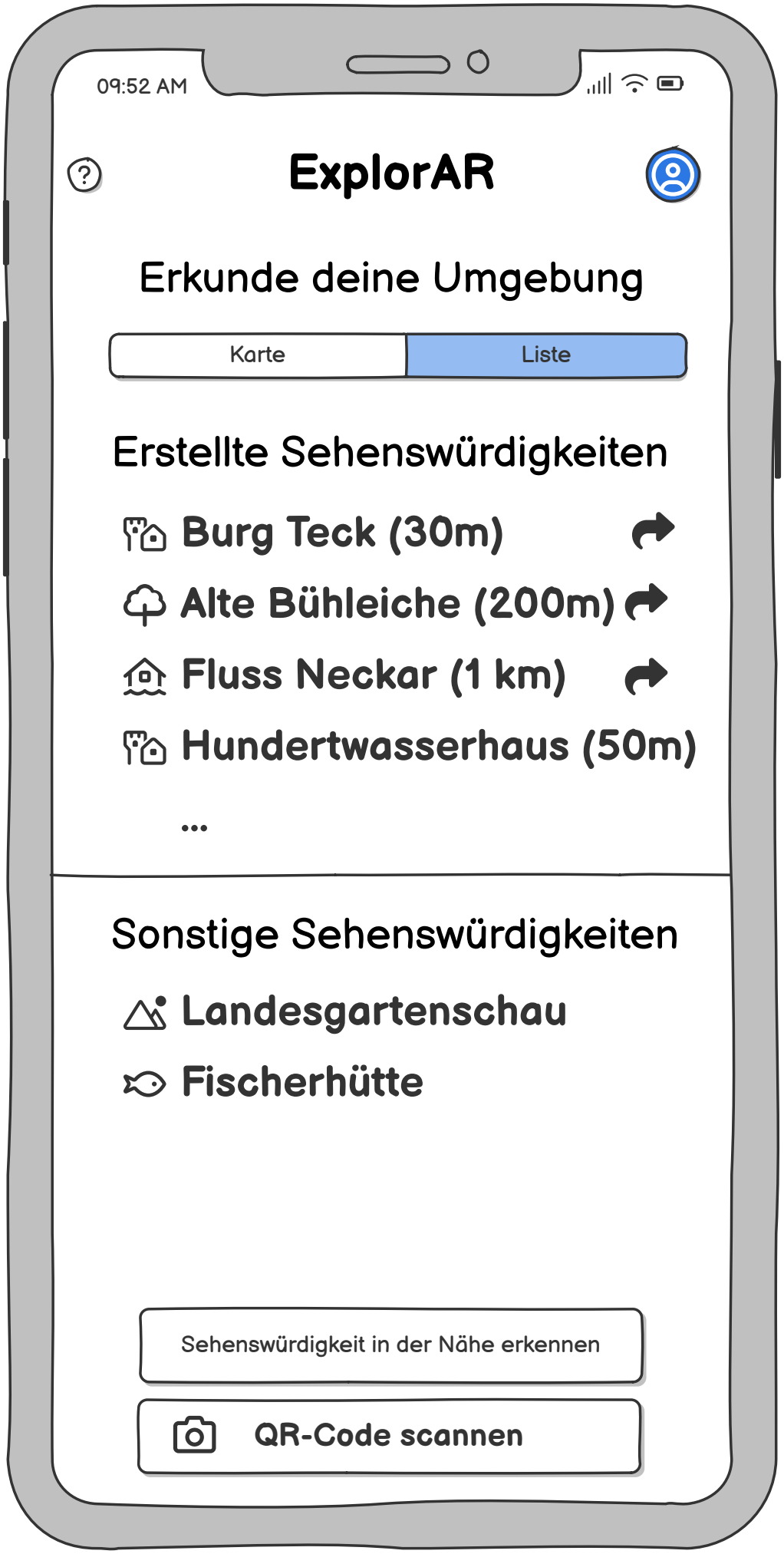

Notiz:

Liste zum Auswählen und Navigieren (Pfeil) zu einer Sehenswürdigkeit.

Erstellte Sehenswürdigkeiten wurden von Ortszugehörigen erstellt.

Die aktuelle Liste zeigt sonstige Sehenswürdigkeiten und deren aktuelle Lage an, die die KI gefunden hat und noch nicht von Menschen aufbereitet wurden.

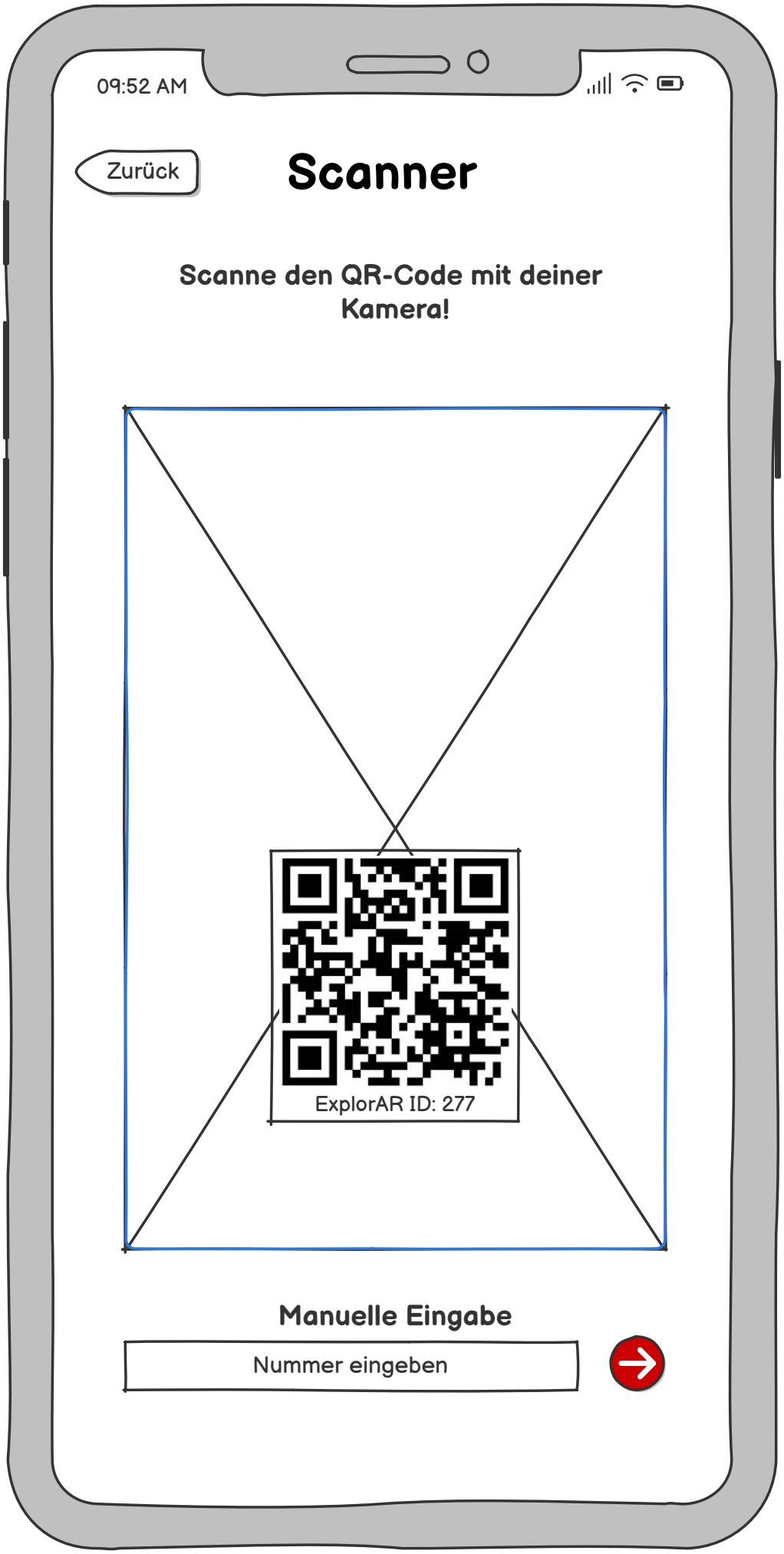

Notiz:

QR Code ist auf einem Schild oder ähnlichem befestigt und kann gescannt werden.

Wenn ID aus QR Code gelesen wurde, wird der Anwender direkt weitergeleitet.

Der Code kann auch manuell im Textfeld eingegeben werden.

Blau: Kameraansicht

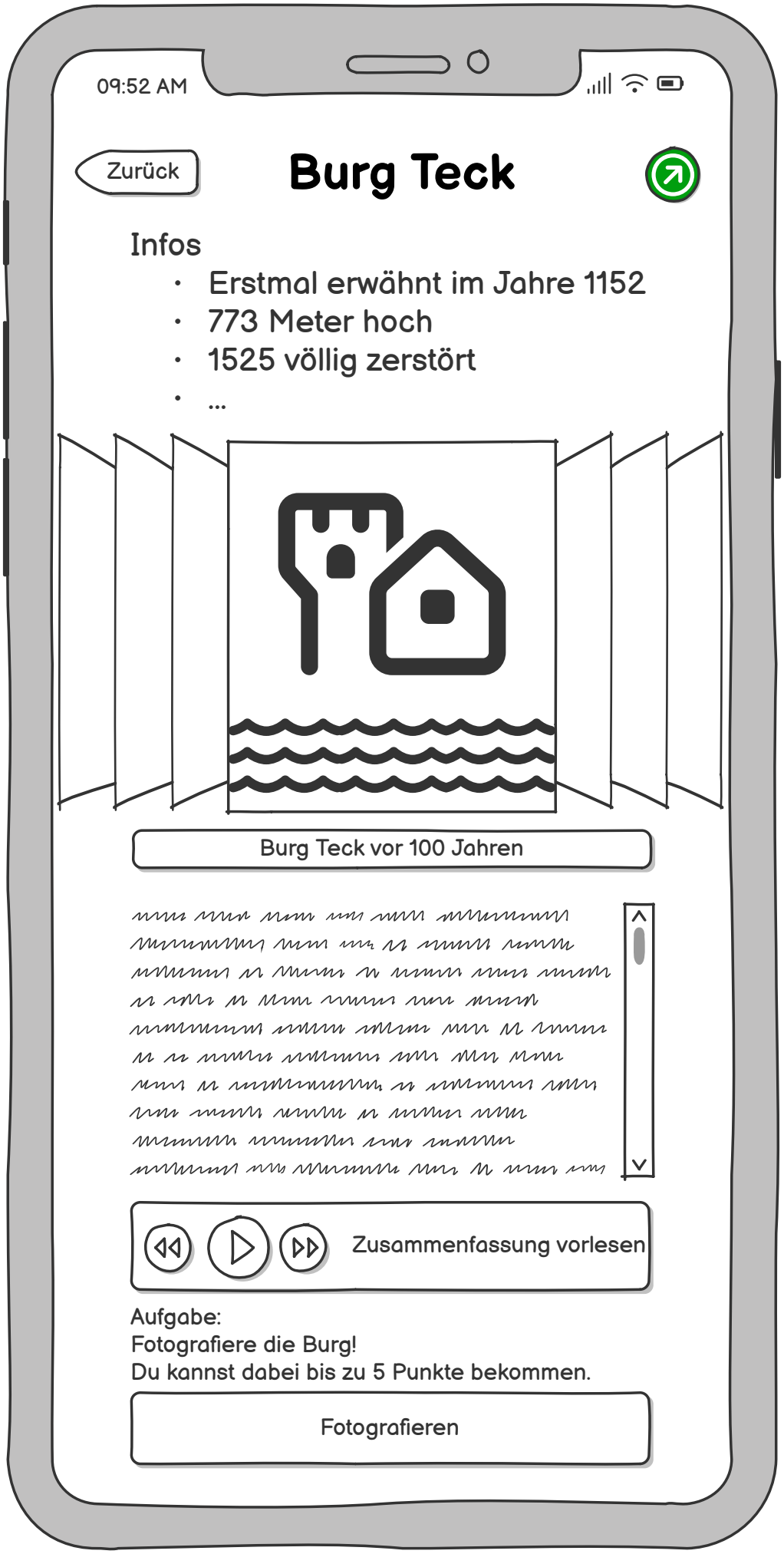

Notiz:

Infos werden z.B mithilfe von KI generiert und die wichtigen Details werden stichwortartig aufgeführt.

Unter dem Bild wird ein ausführlicher länger Text angezeigt.

Button "Burg Teck vor 100 Jahren" zeigt wie es früher ausgesehen haben könnte (KI erstellt).

Zu den Sehenswürdigkeiten gibt es Aufgaben und Spiele, die von Ortsangehörigen erstellt wurden.
Hier z.B. vergibt die KI Punkte für das hochgeladene Bild.

Grüner Knopf leitet hier zur AR Aufgabe hier weiter.

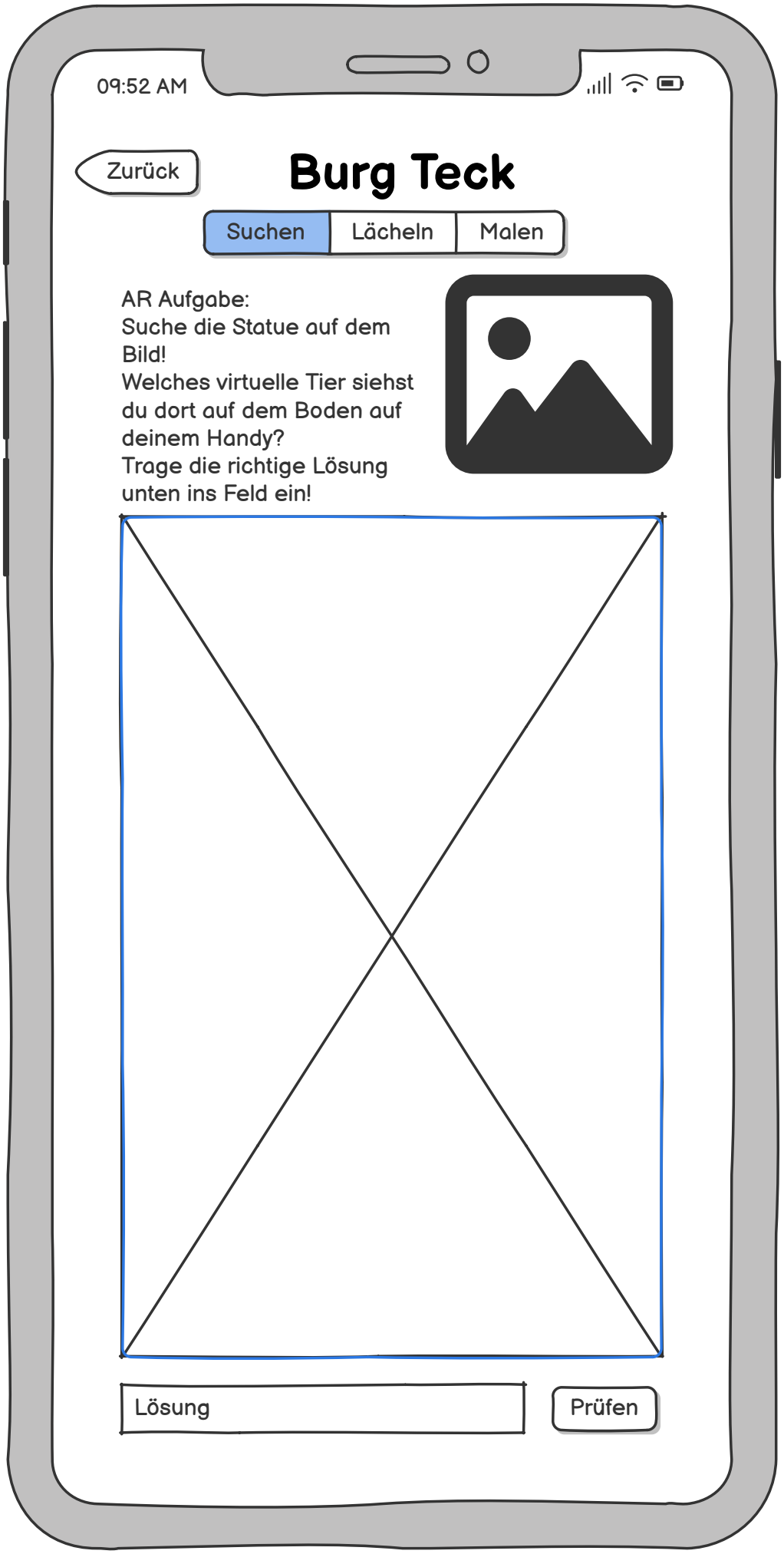

Notiz:

Die Button Bar (Suchen, Lächeln, Malen) ist hier nur für Demozwecke inkludiert um den Klickdummy zu vereinfachen.

Blau: Kameraansicht

Notiz:

Die Button Bar (Suchen, Lächeln, Malen) ist hier nur für Demozwecke inkludiert um den Klickdummy zu vereinfachen.

Blau: Kameraansicht

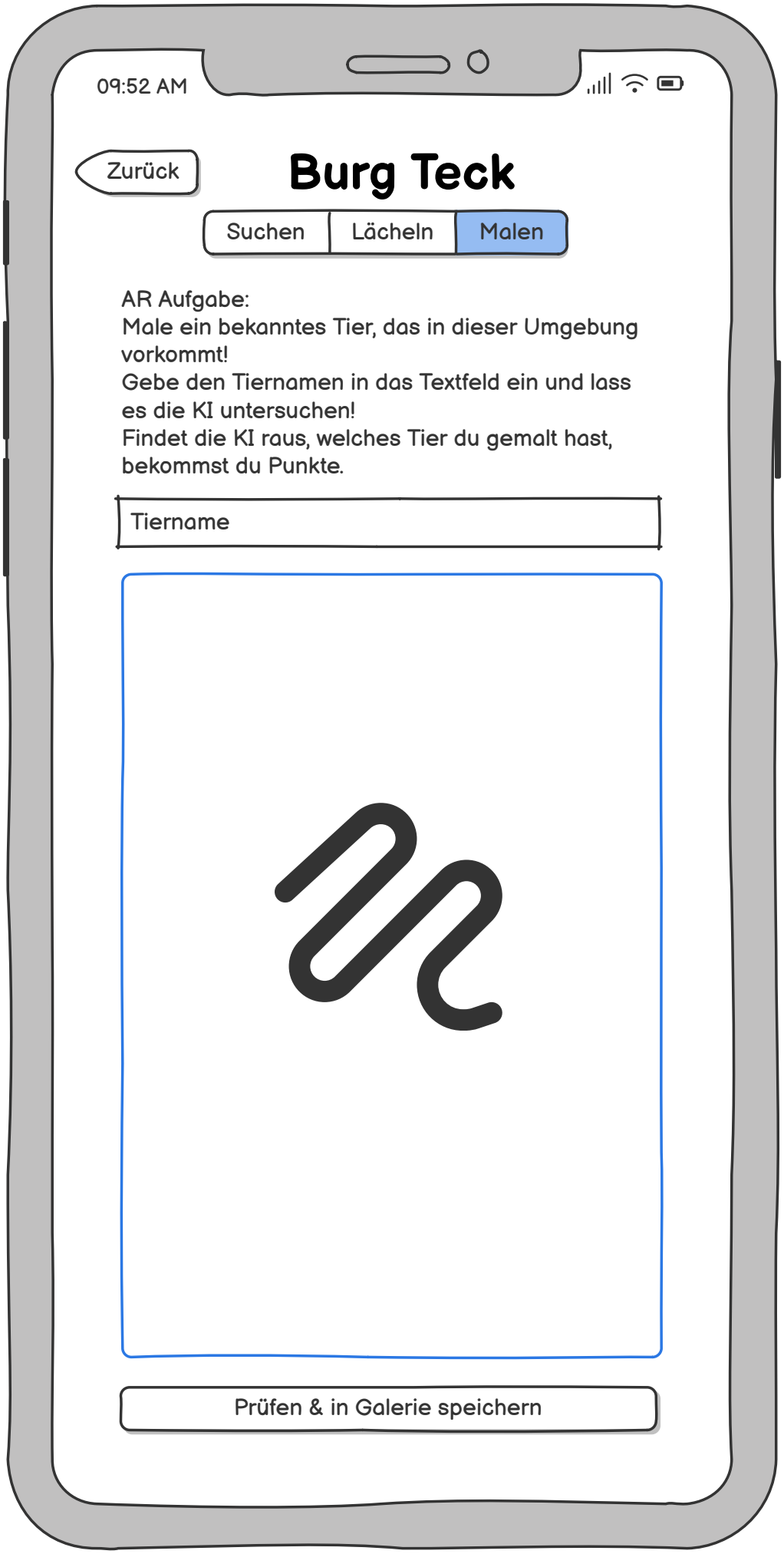

Notiz:

Die Button Bar (Suchen, Lächeln, Malen) ist hier nur für Demozwecke inkludiert um den Klickdummy zu vereinfachen.

Blau: Kameraansicht

09:52 AM

Zurück

250 Punkte

Ortsangehörige | Reisende

Heutige Aufgaben

- [ ] 1/2 Sehenswürdigkeiten besucht (80 Punkte)
- [x] 1 Selfie hochgeladen (60 Punkte)

Heutige Punkte: 60

Wöchentliche Aufgaben

- [ ] 4/8 Sehenswürdigkeiten besucht (80 Punkte)
- [x] 4 Bilder hochgeladen (100 Punkte)
- [ ] 2 Tage infolge 1 Besuch (30 Punkte)

Wöchentliche Punkte: 100

Monatliche Aufgaben

- [ ] 1/2 Orte besucht (200 Punkte)
- [x] 1 Ort bewertet (120 Punkte)

Monatliche Punkte: 120

Notiz:

Die Button Bar (Ortsangehörige und Reisende) ist hier nur für Demozwecke inkludiert um den Klickdummy zu vereinfachen.

Reisende können hier ihre Punkte und Aufgaben einsehen.

09:52 AM

Zurück

220 Punkte

Ortsangehörige | Reisende

Monatliche Aufgaben

- [ ] 1/2 Sehenswürdigkeiten überprüft (20 Punkte)
- [x] 1 neues Bild/Aktion hinzugefügt (40 Punkte)
- [ ] Neue Sehenswürdigkeit erstellt (80 Punkte)
- [ ] Sehenswürdigkeit mit Aktion ergänzt (40 Punkte)
- [ ] 1/2 Erweiterungen überprüft (20 Punkte)
- [ ] Quiz erstellt (50 Punkte)

Meine erstellten Sehenswürdigkeiten

- [ ] Burg Teck (2/3 Überprüfungen)
- [x] Waldsee (freigegeben)

Sehenswürdigkeiten erweitert

- [x] Burg Esslingen: 2 Bilder
- [x] Hundertwasserhaus: 1 Aktion
- [-] Fischerhütte: 1 Bild (In Prüfung: 1/2)

Neue Sehenswürdigkeit erstellen

Sehenswürdigkeit überprüfen

Sehenswürdigkeit erweitern

Du bist als Ersteller in Esslingen eingetragen.

Notiz:

Die Button Bar (Ortsangehörige und Reisende) ist hier nur für Demozwecke inkludiert um den Klickdummy zu vereinfachen.

Ortsangehörige können hier ihre Punkte und Aufgaben etc. einsehen.

Berechtigte Ortsangehörige können mitwirken, indem Sie Sehenswürdigkeiten erstellen und von anderen erstellte Sehenswürdigkeiten begutachten, erweitern und genehmigen.

Von anderen Ortsangehörigen erstellte Sehenswürdigkeiten auf deren Richtigkeit prüfen.

Vorhandene Sehenswürdigkeiten mit Inhalten ergänzen.

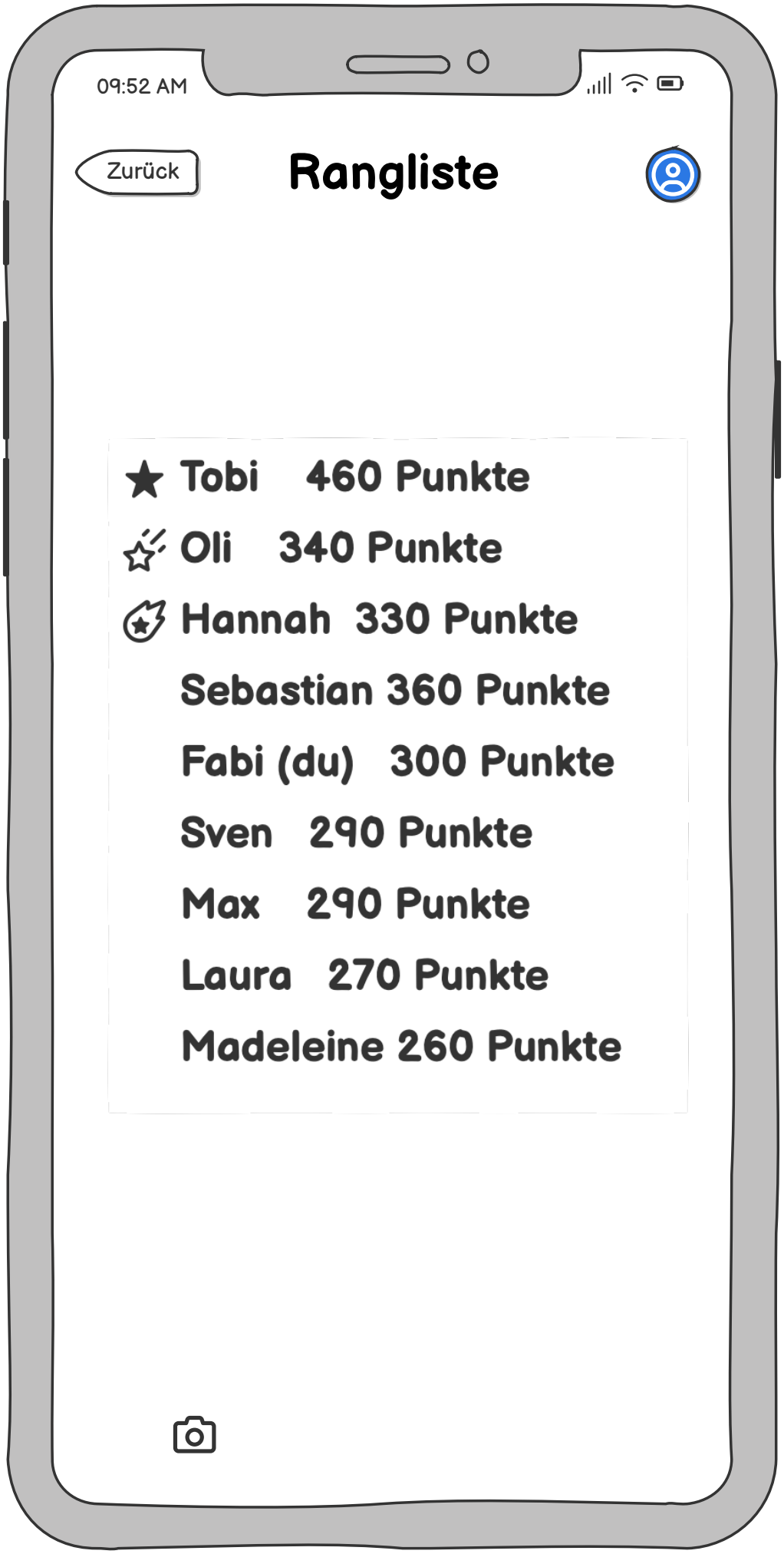

Notiz:

Rangliste der Freunde